CHALLENGE

Souvenir bucolique

Oh ! Je viens de retomber sur cette photo prise à côté d'une charmante petite église...

Quelle banque opérait le distributeur de billet se trouvant dans la cabane au toit herboré ?

Que peut-on maintenant trouver sur l'ancien stade de foot de ce village ?

Format du flag : credit-agricole_baby-foots

WRITE-UP

On fait un Google Lens sur la photo.

On ne retrouve pas de correspondance exacte mais la piste des Iles Feroes semble la plus probable

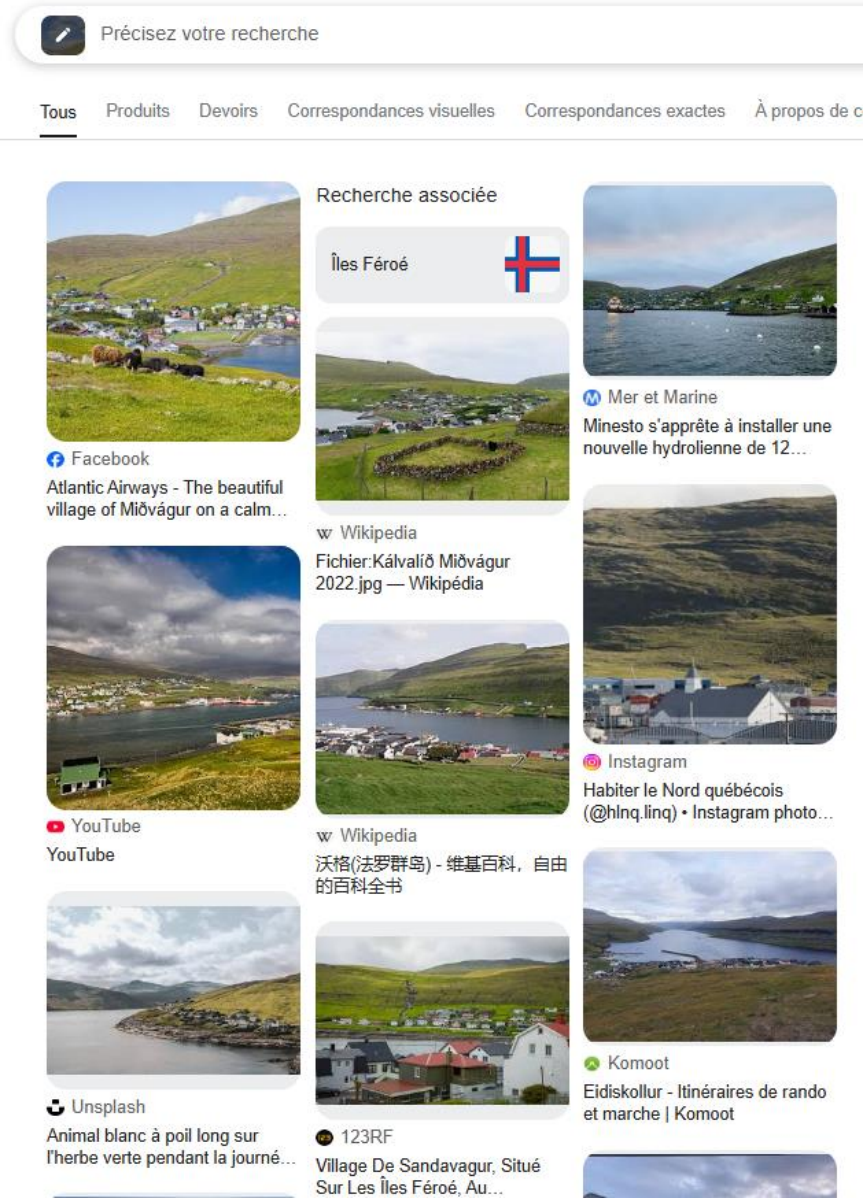

Plusieurs indices sur la photo et dans l'énoncé nous permettent de faire un overpass turbo sur la zone des Féroés :

- Eglise
- Parking
- Cimetiere
- Stade de foot avec projecteurs

On peut par exemple chercher avec la requête suivante :

[out:json][timeout:300]; {{geocodeArea:Îles Féroé}}->.searchArea;

(nwr"building"="church";)->.church;

(nwr(around.church:50)["amenity"="parking"];)->.park;

(nwr(around.park:100)["leisure"="pitch"]["sport"="soccer"]["lit"="yes"];)->.terrain;

(.terrain;);

out geom;

Ce qui nous donne :

```
[out:json][timeout:300];
{{geocodeArea:Îles Féroé}}->.searchArea;

(
  nwr["building"="church"](area.searchArea);
)->.church;

(
  nwr(around.church:50)["amenity"="parking"];
)->.park;

(
  nwr(around.park:100)["leisure"="pitch"]["sport"="soccer"]["lit"="yes"];
)->.terrain;

(.terrain;);

out geom;
```

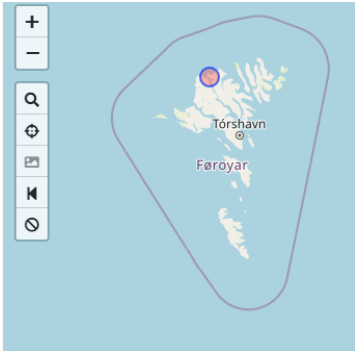

On zoome alors sur le point défini et on retrouve bien les éléments définis en concordance avec la photo (on peut aussi vérifier via Maps que l'on est au bon endroit)

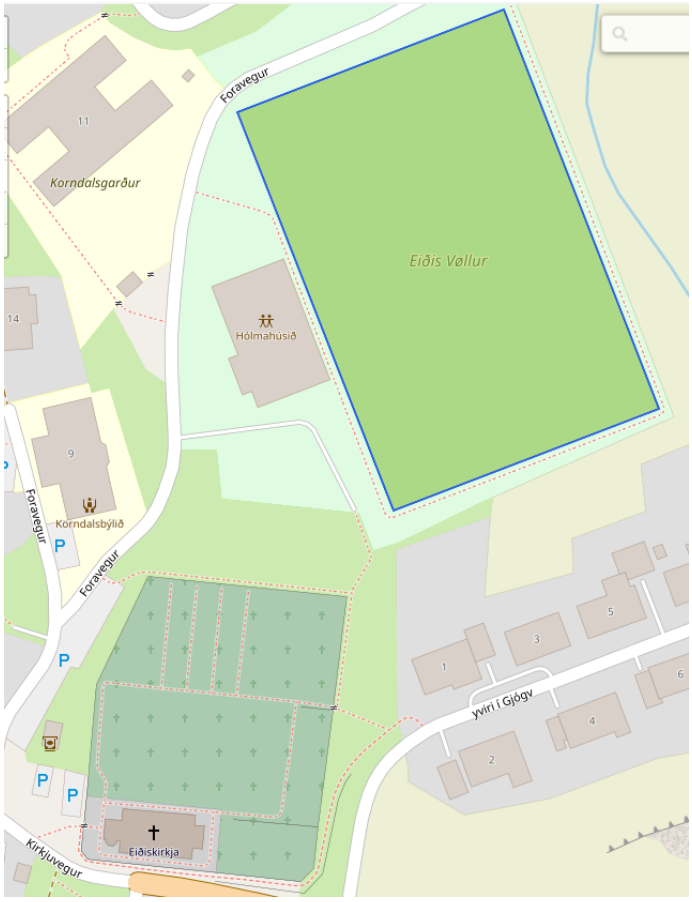

En zoomant encore sur la cabane, on trouve la réponse à la première question

La première partie du flag est donc : bank-nordik

Nous avons également le stade mais rien ne saute aux yeux sur overpass turbo

Nous avons le nom du village : Eiði

Nous faisons donc une recherche Google

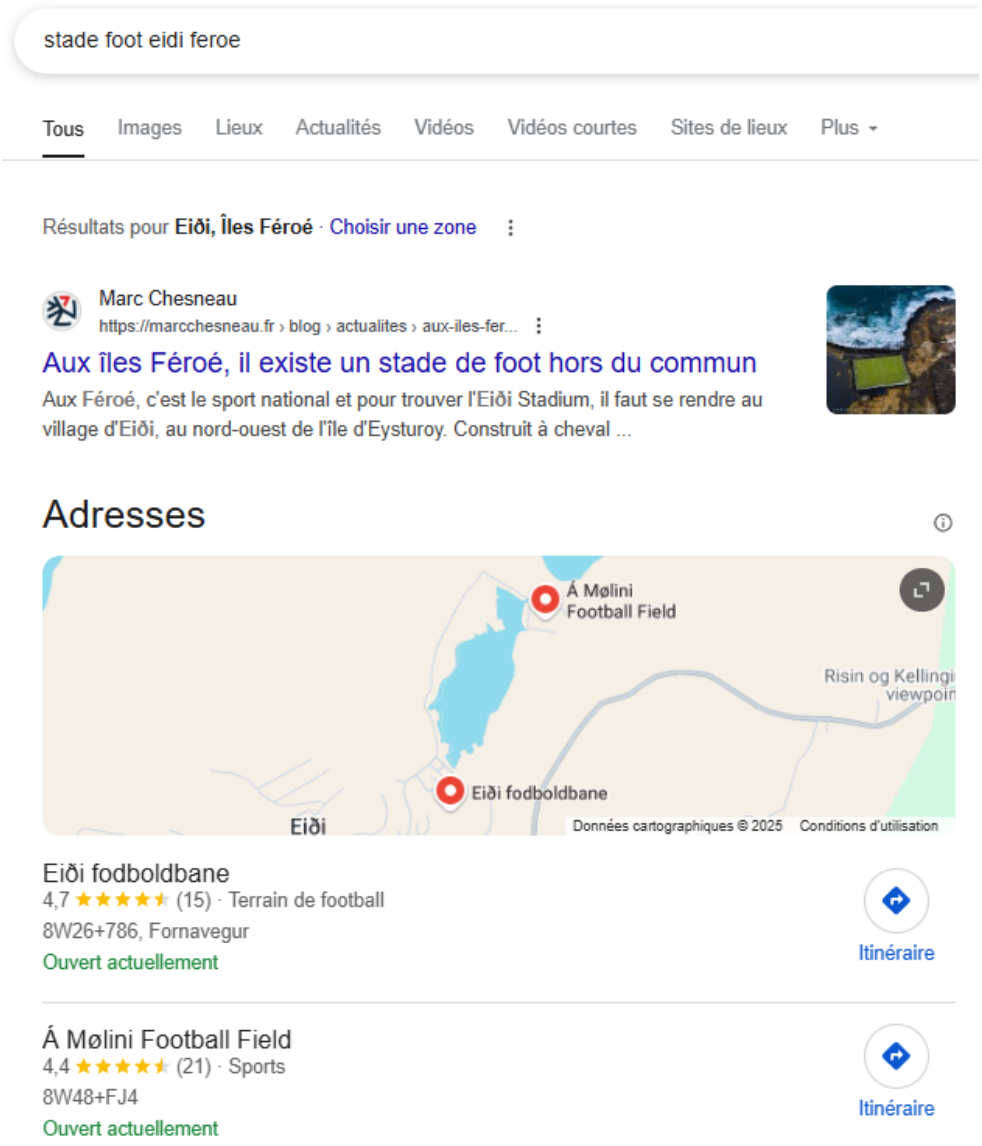

On se rend compte qu'il y a deux stades et l'un des deux semble "spécial"

En allant sur le premier lien, on voit que l'ancien stade est plus au nord en bord de mer et que c'est devenu un camping

De nos jours, le stade s'est transformé en camping !

En vérifiant sur maps, ou en regardant la vidéo sur https://elements.envato.com/fr/abandoned-football-pitch-eidi-campsite-on-faroe-is-T42KZU8 ou d'autres sites, on voit que c'est bien un camping rempli principalement de camping-cars

NB : On aurait aussi pu le voir en zoomant / dézoomant sur overpass turbo

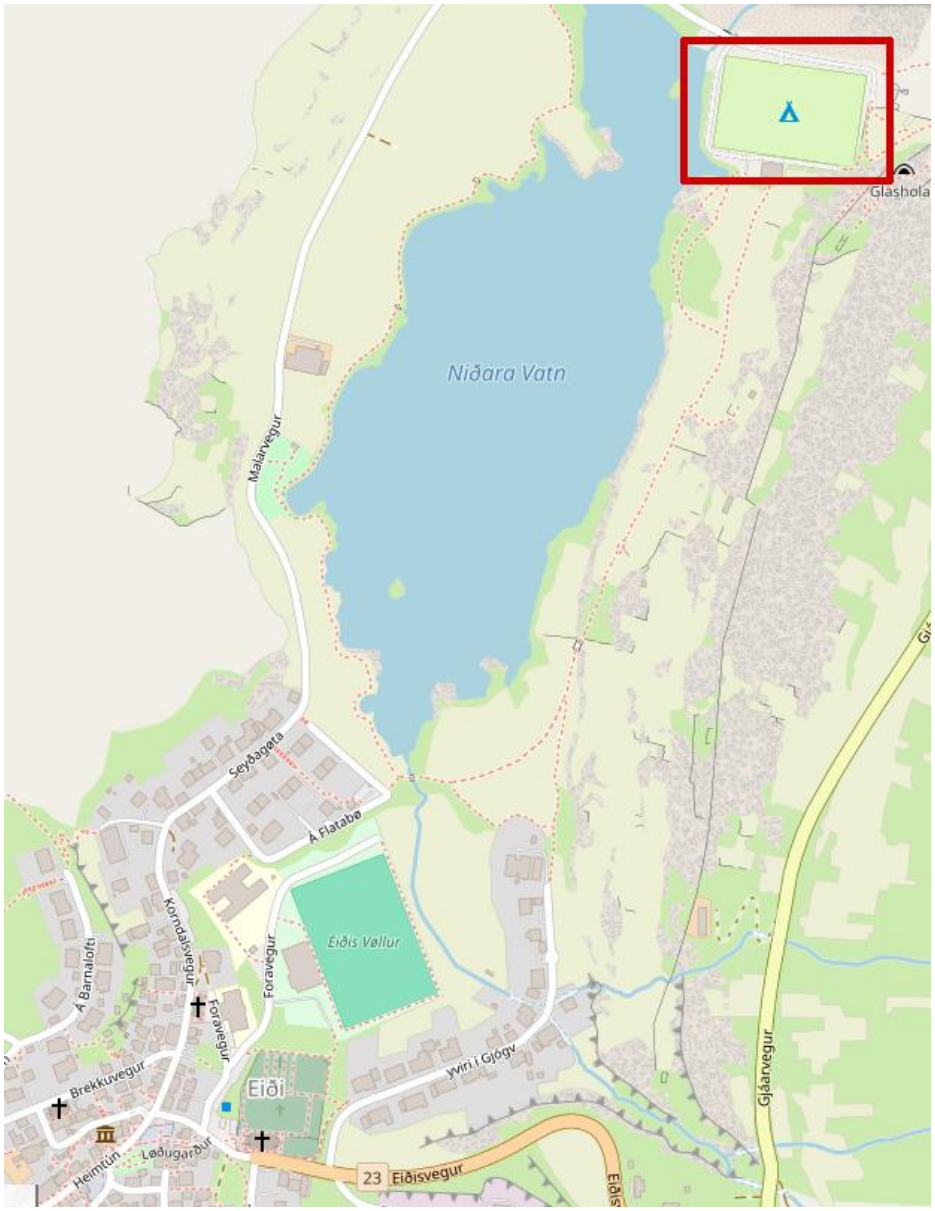

FLAG : bank-nordik_camping-cars